VISU2.1.5 Accès aux vues

La vue sur l'extérieur assure une connexion visuelle avec l'environnement extérieur pour fournir des informations sur l'environnement local, les changements météorologiques et l'heure de la journée. Ces informations peuvent alléger la fatigue associée à de longues périodes passées à l'intérieur. Il convient que tous les occupants d'un espace aient la possibilité de se ressourcer et de se détendre grâce à un changement de cadre et de perspective. Il convient d'évaluer la vue sur l'extérieur à partir de points de référence sélectionnés correspondant à la position des personnes dans la surface utile.

Une vue est considérée comme comprenant trois composantes distinctes :

- une composante de ciel ;
- une composante de paysage ;
- une composante de sol.

Note : La composante de sol peut fournir des informations sur les activités. La composante de paysage peut comprendre des bâtiments, la nature et/ou l'horizon uniquement.

À partir de tout point de référence spécifique (Q), la qualité de la vue dépend :

- des dimensions de la (des) prise(s) de jour ;
- de la largeur de la vue (angle de vision horizontal) ;
- de la distance extérieure de la vue ;
- du nombre de composantes visibles ;
- de la qualité de la vue sur l'environnement extérieur.

L'indicateur « accès aux vues », inspiré de la norme EN 17037 « Lumière naturelle dans les bâtiments » de décembre 2018, se décompose en 3 critères : l'angle de vue, la distance de vue et la composante de vue. Dans cette exigence, seuls 2 critères sont pris en compte : la distance de vue et la composante de vue.

Les atriums peuvent être considérés comme des espaces extérieurs pour cet indicateur « accès aux vues ». Ainsi une vue sur un patio couvert doit être évaluée.

Pour avoir accès à chacun des deux indicateurs de l'exigence « accès aux vues », trois cas de figure :

- le logiciel les fournit directement : dans ce cas, l'environnement dans un rayon d'au moins 50 m devra faire partie du modèle 3D.
- détermination "manuelle" : à partir de plans et coupes on estime les distances maximales et les composantes.
  Note : Utilisation d'un objectif grand angle pour réduire, dans tous les cas, à une ou deux photos permettant de déterminer ce que l'on voit par l'ensemble des ouvertures.
- pour un bâtiment existant : ces informations peuvent être évaluées sur la base de photos in-situ et de plans.

Pour déterminer l'indicateur 'Accès aux vues", on considère un observateur positionné aux trois quarts de la profondeur normale à la façade et au niveau du milieu de cette façade et le regard (hauteur à 1,30 m du sol) dirigé vers la façade concernée.

- Note 1 : Dans le cas d'une « Zone « entrepôt » hors entrepôt frigorifique », la zone à considérer est la zone de préparation.
- Note 2 : Si le positionnement des postes de travail est connu, alors il est possible de réaliser le calcul en considérant un point focal défini par le demandeur. Le positionnement dépend du nombre de façades vitrées éclairant le local considéré. Dans ce cas, en présence d'ouverture sur plusieurs parois, le point de référence reste le même, contrairement à ce qui est précisé sur les schémas ci-dessous.

Cas d'ouvertures sur plusieurs parois :

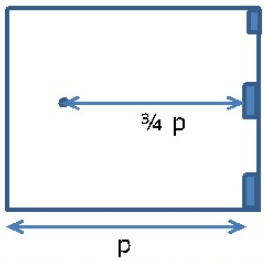 **Ouvertures sur une seule façade** Au ¾ de la profondeur Au milieu de la façade vitrée	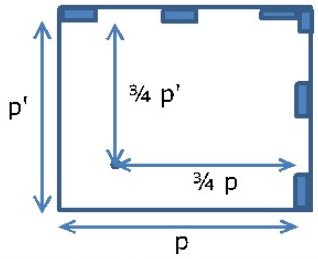 **Ouvertures sur deux façades** Au ¾ de la profondeur 1 Au ¾ de la profondeur 2
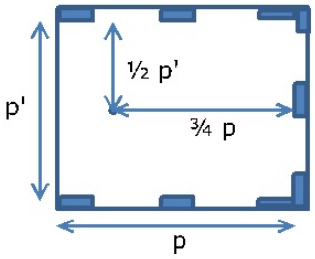 **Ouvertures sur trois façades** Au ¾ de la profondeur 1 À la moitié de la profondeur 2	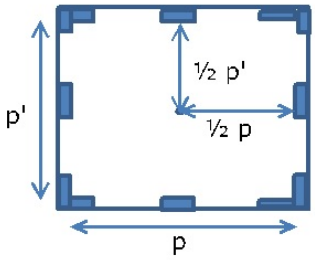 **Ouvertures sur quatre façades** À la moitié de la profondeur 1 À la moitié de la profondeur 2

L'évaluation se fait selon le tableau suivant :

Calcul du nombre de points "Accès aux vues"		
Distance de vue	**Composantes de vue**	Points
> 50 m	Les trois	6
]20 m – 50 m]	Deux des trois	5
]6 m – 20 m]	Paysage	4
]0 m – 6 m]	Ciel seul OU sol seul	3
0 m (*)	Aucune (*)	0

(*) : Locaux aveugles

Nombre de points "Accès aux vues" = Somme des points (Distance de vue + Composantes de vue)

Détermination de la distance aux vues

La distance de vue est la distance entre la façade et les premiers obstacles vus depuis chacune des ouvertures. La végétation n'est pas à considérer comme un obstacle à cette vue. La taille des végétaux à prendre en compte est la taille nominale. Si des obstacles sont vus à des distances différentes, prendre le cas le plus défavorable.

Détermination des composantes de vue

La présence de l'élément suffit à valider le critère.

Situation	Niveaux	Composante de vue
Ruelle" ou petite cour intérieure	Premiers et derniers étages	Deux des trois
	Étages intermédiaires	Paysage
Urbain dense	RdC et derniers étages	Deux des trois
	Étages intermédiaires	Paysage
Urbain	RdC et derniers étages	Deux des trois
	Étages intermédiaires	Paysage
Péri-urbain et "campagne"	Tous niveaux	Les trois

- La taille des végétaux à prendre en compte est la taille nominale.
- Dans le cas d'une justification par plans :
  - Si des masques (bâtiments et/ou végétaux) peuvent être vus depuis la position de l'observateur depuis les ouvertures, cela signifie qu'au moins la composante paysage est vue.
  - Si dans une direction par une des fenêtres, on ne voit pas de masques (bâtiments et/ou végétaux), cela signifie que le sol et le ciel sont vus (pas le paysage).

Si dans toutes les directions des masques (bâtiments et/ou végétaux) peuvent être vus, alors il faut passer en « mode coupe » pour savoir si ciel et sol peuvent aussi être vus.

Distances :

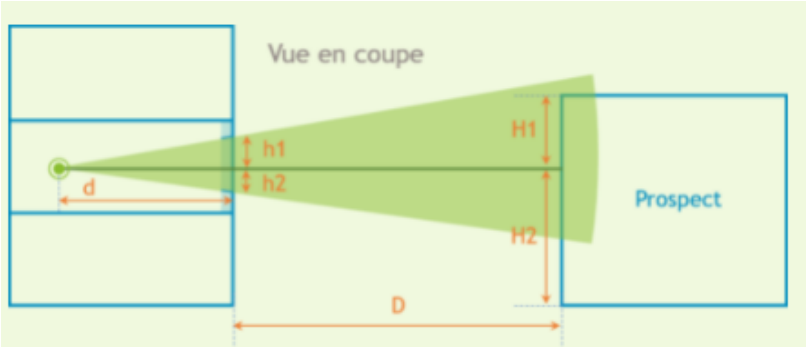

- D : distance entre la façade vitrée du local et le prospect vu
- h1 : hauteur entre l'œil et la hauteur sous linteau
- h2 : hauteur entre l'œil et la hauteur d'allège
- H1 : hauteur entre l'œil et le sommet du prospect
- H2 : hauteur entre l'œil et la base du prospect

On considère que le ciel est vu si: $H1<h1(D+d)/d$

On considère que le sol est vu si: $H2<h2(D+d)/d$

IMPORTANT : Pour les bâtiments en Rénovation ou en Exploitation Axe Bâtiment :

- Le niveau E (4 points) est atteint si l'article R4223-3 du Code du Travail est respecté. Pour information, la lettre-circulaire DRT n° 90/11 du 28 juin 1990 précise certains points (voir annexe 2).
- Pour atteindre un niveau supérieur, un calcul d'accès aux vues respectant les conditions ci-dessus doit être réalisé.

Pour les bâtiments en exploitation Axe Gestion : Cet indicateur n'est pas pris en compte.

NOTATION

- Les points attribués sont donnés dans les tableaux par type de local dans la partie « Echelles d'évaluation » de ce document : 0, 4, 8, 12, 16 ou 20 points.